Detaljregulering for Vedderheia Nord Felt B22 i Søgne kommune

PLANBESKRIVELSE

PlanID: 201602
Dato: 02.06.2016

3647

Utarbeidet for: REPSTAD EIENDOM AS
Utarbeidet av: VIANOVA KRISTIANSAND AS

Innholdsfortegnelse

1 SAMMENDRAG 4

2 BAKGRUNN 4

2.1 HENSIKTEN MED PLANEN 4
2.2 FORSLAGSTILLER, PLANKONSULENT, EIERFORHOLD 4
2.3 TIDLIGERE VEDTAK I SAKEN 5
2.4 UTBYGGINGSAVTALER 5
2.5 UTREDNINGER 5
2.6 VEDLEGG 5

3 PLANPROSESSEN 5

4 PLANSTATUS OG RAMMEBETINGELSER 6

4.1 OVERORDNEDE PLANER 6
4.2 GJELDENDE REGULERINGSPLANER 6
4.3 TILGRENSENDE PLANER 7
4.4 TEMAPLANER 7
4.5 STATLIGE PLANRETNINGSLINJER/RAMMER/FØRINGER 7

5 BESKRIVELSE AV PLANOMRÅDET, EKSISTERENDE FORHOLD 8

5.1 BELIGGENHET 8
5.2 DAGENS AREALBRUK OG TILSTØTENDE AREALBRUK 9
5.3 STEDETS KARAKTER 9
5.4 LANDSKAP 9
5.5 KULTURMINNER OG KULTURMILJØ 9
5.6 NATURMANGFOLD 10
5.7 REKREASJONSVERDI/ REKREASJONSBRUK, UTEOMRÅDER 12
5.8 LANDBRUK OG KULTURLANDSKAP 12
5.9 TRAFIKKFORHOLD 12
5.10 BARNS INTERESSER 13
5.11 SOSIAL INFRASTRUKTUR 13
5.12 UNIVERSELL TILGJENGELIGHET 14
5.13 TEKNISK INFRASTRUKTUR 14
5.14 GRUNNFORHOLD 14
5.15 STØYFORHOLD 15
5.16 RISIKO- OG SÅRBARHET (EKSISTERENDE SITUASJON) 15

6 BESKRIVELSE AV PLANFORSLAGET 16

6.1 PLANLAGT AREALBRUK 16
6.2 GJENNOMGANG AV AKTUELLE REGULERINGSFORMÅL 16
6.3 BEBYGGELSENS PLASSERING OG UTFORMING 17
6.4 BOLIGMILJØ/ BOKVALITET 18
6.5 FOLKEHELSELOVEN 18
6.6 PARKERING 20
6.7 TILKNYTNING TIL INFRASTRUKTUR 21
6.8 TRAFIKKLØSNING 21
6.9 PLANLAGTE OFFENTLIGE ANLEGG 22
6.10 MILJØOPPFØLGING 22
6.11 UNIVERSELL UTFORMING 22
6.12 UTEOPPHOLDSAREAL 22
6.13 LANDBRUKSFAGLIGE VURDERINGER 23
6.14 KOLLEKTIVTILBUD 23
6.15 KULTURMINNER 23
6.16 PLAN FOR VANN- OG AVLØP SAMT TILKNYTNING TIL OFFENTLIG NETT 23
6.17 AVBØTENDE TILTAK/ LØSNINGER ROS 24

6.18 REKKEFØLGEBESTEMMELSER 24

7 VIRKNINGER/KONSEKVENSER AV PLANFORSLAGET 25

7.1 OVERORDNEDE PLANER 25
7.2 LANDSKAP/BEBYGGELSE 25
7.3 STEDETS KARAKTER 25
7.4 ESTETIKK 25
7.5 KULTURMINNER OG KULTURMILJØ, EVT. VERNEVERDIER 25
7.6 FORHOLDET TIL KRAVENE I KAP II I NATURMANGFOLDLOVEN 25
7.7 REKREASJONSINTERESSER/ REKREASJONSBRUK 26
7.8 UTEOMRÅDER 26
7.9 TRAFIKKFORHOLD 26
7.10 BARNS INTERESSER 27
7.11 SOSIAL INFRASTRUKTUR 27
7.12 UNIVERSELL TILGJENGELIGHET 28
7.13 ENERGIBEHOV - ENERGIFORBRUK 28
7.14 ROS 28
7.15 TEKNISK INFRASTRUKTUR 28
7.16 DRIFT OG VEDLIKEHOLD 28
7.17 ØKONOMISKE KONSEKVENSER FOR KOMMUNEN 28

8 INNKOMNE INNSPILL 29

9 AVSLUTTENDE KOMMENTAR 31

1 Sammendrag

ViaNova Kristiansand AS har på vegne av Repstad Eiendom AS, utarbeidet detaljregulering Vedderheia Nord felt B22 i Søgne kommune.
Detaljplanen er basert på reguleringsplan Vedderheia Nord.

Detaljregulering felt B22 har følgende hovedmål:

- Skape et godt og attraktivt boligområde.
- Sør- og vestvendte tomter
- Regulere snarveg/sti og grønnstruktur.

Planområdet omfatter 22 nye boliger.

I gjeldende reguleringsplan er hele planområdet regulert til «boligbebyggelse» og «friluftsområde». Atkomst til planområdet er fra sørøst ved hovedvegen Vedderheia. Planområdet er regulert med boligtomter på hver side av atkomstvegen. Boligtomtene er vendt mot vest og sør og har utsikt utover Repstadvannet. Det reguleres også friområde med snarveger/stier til turområder, bussholdeplass og til Repstadvannet. Planområdet har kort avstand til et større lekeområde FR3 i reguleringsplan for Vedderheia Nord.

Det ble meldt oppstart av planarbeidet i februar 2016, med brev til berørte parter og annonse i avisa Søgne- og Songdalen Budstikke.

Informasjon vil bli tilgjengelig på Søgne kommunes internettside (www.sogne.kommune.no).

2 Bakgrunn

2.1 Hensikten med planen

I bestemmelsene til reguleringsplanen Vedderheia nord, kreves det detaljregulering for felt B22. Detaljplanen tilrettelegger i hovedsak nye arealer til boligområder, infrastruktur og grønnstruktur.

2.2 Forslagstiller, plankonsulent, eierforhold

Tiltakshaver:

- Repstad Eiendom AS, Birkedalsveien 80, 4640 Søgne.
  Tiltakshavers kontaktperson er Ole Johan Bueklev.

Rådgivende ingeniørfirma:

- ViaNova Kristiansand AS, Pb. 541, 4665 Kristiansand.
  Prosjektansvarlig er Anita Wiberg Gjelsten.
  Prosjektmedarbeidere: Even F. Lorentsen, Tore A. Nilsen og Marry Sjøvold.
- Feste Grenland AS, Pb. 120, 3901 Porsgrunn.
  Prosjektmedarbeider landskapsarkitekt Pål Mæhlum.

Planforslaget viser ny kommunal veg, parkeringsplass og offentlig friområde. Dette innebærer at en del tidligere private arealer, nå blir i offentlig eie.

2.3 Tidligere vedtak i saken

Det er ikke utarbeidet tidligere vedtak med administrasjonen i Søgne kommune.

2.4 Utbyggingsavtaler

Det er foreløpig ikke utarbeidet utbyggingsavtale. Prosessen med utbyggingsavtale mellom tiltakshaver og Søgne kommune går parallelt med detaljplanen, og kan tidligst godkjennes samtidig med at detaljreguleringsplanen godkjennes i kommunestyret.

2.5 Utredninger

Det er ikke behov for utredninger i detaljreguleringsplanen.

2.6 Vedlegg

- Plankart
- Bestemmelser
- ROS
- Tekniske planer for Veg og VA
- Snitt av området
- Illustrasjonsplan
- Mottatte merknader
- Oppstarts varsel (brev og annonse)

3 Planprosessen

Medvirkningsprosessen har vært delt i to.

- Kommunen og utbygger:

Oppstartsmøte mellom Søgne kommune og tiltakshaver og rådgiver ble avholdt den 20.01.2016.

- Varsel til grunneiere, naboer og etater:

Det ble varslet oppstart av detaljregulering. Det ble annonsert i avisen Søgne- og Songdalen Budstikke den 10.02.2016 samt brev til berørte parter den 05.02.2016.

Grunneierliste ble oversendt av Søgne kommune.

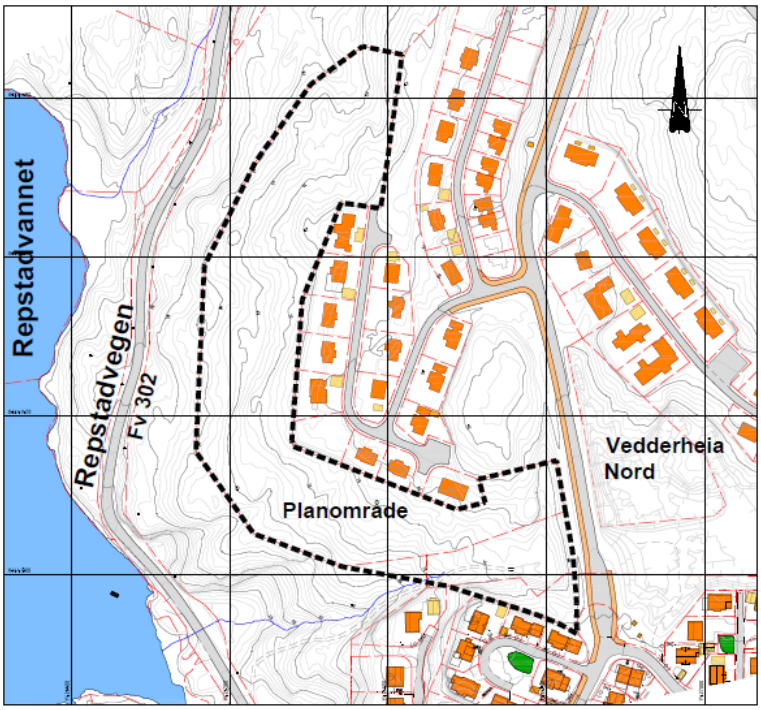

Figur 1, varslet planavgrensning.

4 Planstatus og rammebetingelser

4.1 Overordnede planer

- Kommuneplanens arealdel:

I bestemmelsene og retningslinjene er det gitt generelle krav til funksjonskrav og utbyggingsvolum. Det er rekkefølgebestemmelser for etablering av nytt kryss til E39.

4.2 Gjeldende reguleringsplaner

Gjeldende reguleringsplan er «Vedderheia nord», vedtatt 13.01.2010 (planID 20100113). Detaljreguleringen omfatter felt B22 som er regulert til «boliger», samt et område i sørøst som er regulert til friluftsområde.

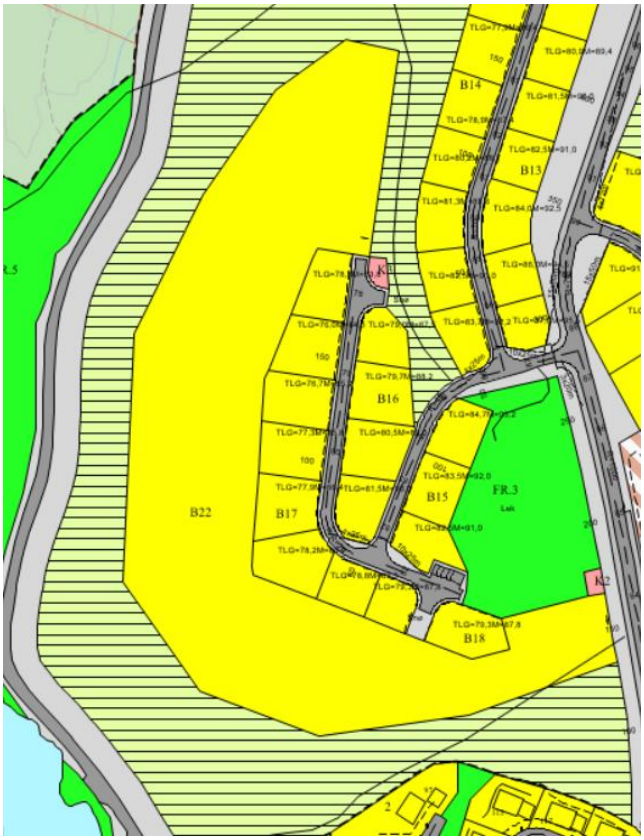

Figur 2, Gjeldende reguleringsplaner, felt B22.

4.3 Tilgrensende planer

Tilgrensende reguleringsplaner er reguleringsplanen «Vedderheia nord», vedtatt 13.01.2010 (planID 20100113). Denne omfatter tilstøtende boliger mot øst og friluftsområder mot sør, vest og nord.
Reguleringsplan «Vedderheia felt E, F og G», vedtatt 04.04.2001 (planID 20010404). Denne planen omfatter tilstøtende boligområde i sør.

4.4 Temaplaner

Det er ikke utarbeidet spesielle temaplaner for denne detaljreguleringsplanen.

4.5 Statlige planretningslinjer/rammer/føringer

Miljøverndepartementets retningslinje grenseverdier for støy, T-1442.
Vannressursloven.
Miljøverndepartementets rundskriv T-2/08 om barn og planlegging.

5 Beskrivelse av planområdet, eksisterende forhold

5.1 Beliggenhet

- Beliggenhet

Planområdet ligger i Søgne kommune, nord for E39 og ca. 2,5 km nord for Lunde sentrum.

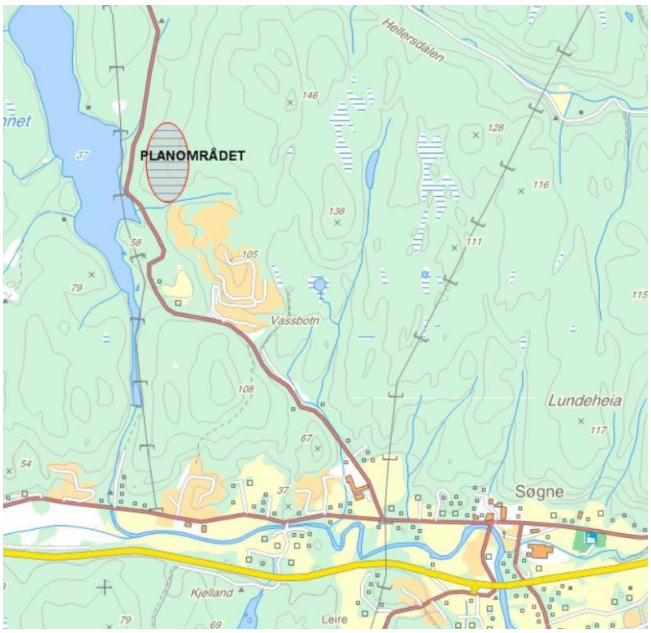

Figur 3, Oversiktskart av planområdet.

Figur 4, skråfoto av planområdet, vestre område

Figur 5, skråfoto av planområdet, søndre område

- Avgrensning og størrelse på planområdet

Området er på totalt ca. 32 daa, og ligger som en bue rundt tilstøtende eksisterende boligområde «B17». Området er skogkledd og terrenget skråner mot vest og sør, med utsikt til Repstadvannet.

5.2 Dagens arealbruk og tilstøtende arealbruk

Planområdet er dekket av skog, og er regulert til «bolig». Vest for planområdet ligger Repstadveien. Øst for planområdet ligger eksisterende boligområde «B17» med tilhørende kommunal veg.

5.3 Stedets karakter

Planområdet består av et skogkledd område, skrånende mot vest og sør. Det er ingen eksisterende bebyggelse innenfor planområdet.

5.4 Landskap

Området er typisk sørlandsk med fine utsiktsforhold mot Repstadvannet. Området ligger solrikt til. Det er et lokalt mildt kystklima og kan være vindutsatt fra vest. Det er ingen spesielle forhold angående estetiske og kulturelle verdier som utpeker seg.

5.5 Kulturminner og kulturmiljø

Fylkeskonservator har tidligere uttalt seg i gjeldende reguleringsplan «Vedderheia nord», og har ingen merknader i forhold til kulturminner og kulturmiljø.
I databasen for kulturminner «Askeladden», er det ikke registrert automatisk fredete fornminner i området.

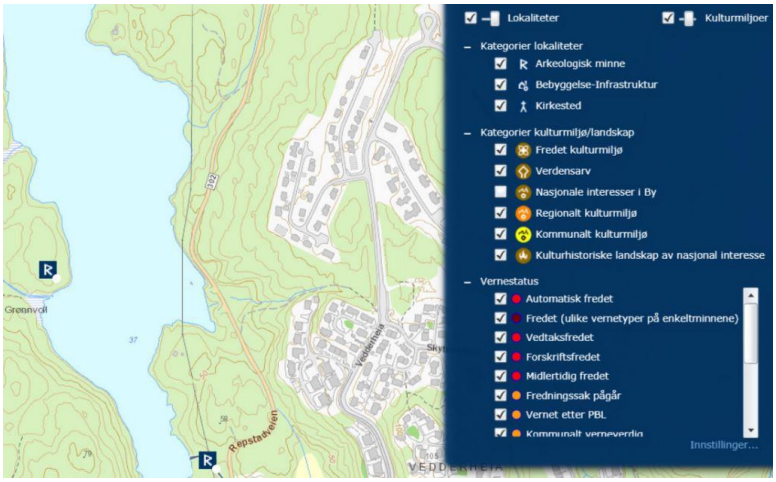

Figur 6, kartutsnitt databasen for kulturminner, Askeladden

5.6 Naturmangfold

GENERELT:
I henhold til naturmangfoldloven § 7 skal prinsippene i NML §§ 8-12 legges til grunn som retningslinjer ved utøving av offentlig myndighet og vurderingene skal fremgå av beslutningen. Kunnskapen om naturmangfold (jf. NML § 8) baserer seg på søk i innsynsløsningene i Norsk institutt for skog og landskap (tidligere del av Skog og landskap) (www.nibio.no), Naturbase (www.naturbase.no), Artsdatabanken (www.artsdatabanken.no), forurensning (miljøstatus) og naturresurser (www.ngu.no). En påvirkning av et økosystem skal vurderes ut fra den samlede belastning som økosystemet er eller vil bli utsatt for

NATURTYPER OG VEGETASJON:
Innenfor planområdet består arealet av barskog med lav til middels bonitet.

Figur 7, kartutsnitt skog og bonitet, NIBO

NATURBASE:
Det er ikke registrert spesielle verdifulle naturtyper, eller arter på rødlista eller svartlista innenfor planområdet.

Figur 8, kartutsnitt Naturbase

ARTSOBSERVASJONER:
I artsdatabanken er det ikke registrert planter eller dyr på svartelista (uønsket) eller på rødlista (sårbar/truede arter).

Figur 9, kartutsnitt Artsdatabanken

FORURENSNING:
I h.h.t. databasen Miljøstatus, er det ingen forurensning av grunnen i planområdet.

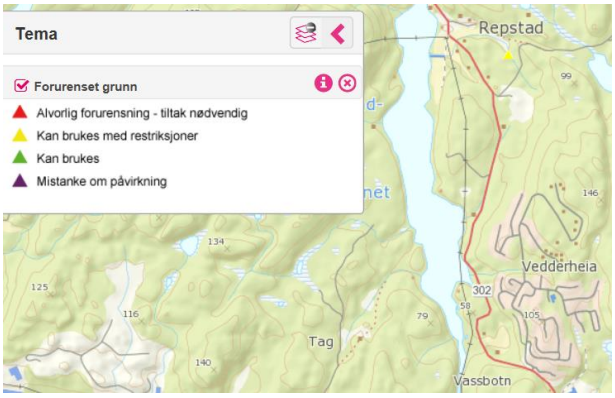

Figur 10, kartutsnitt forurenset grunn, Miljøstatus

NATURRESURSER:
I h.h.t. databasen til NGU for mineralressurser, er det ingen konflikt med registrerte mineralressurser av nasjonal eller regional verdi. Det vises til kart nedenfor.
Det er ingen drivverdige jordressurser i området.

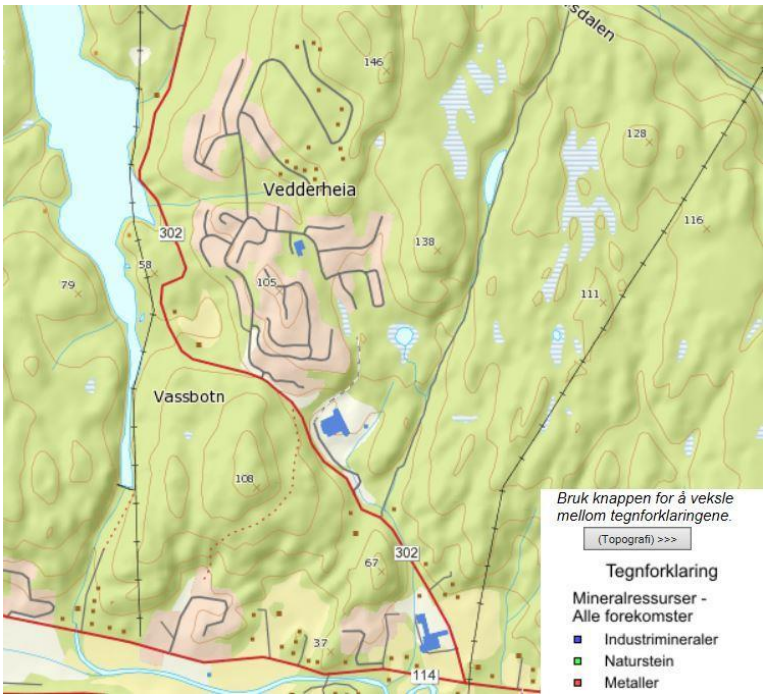

Figur 11, kartutsnitt mineralressurser, NGU

5.7 Rekreasjonsverdi/ rekreasjonsbruk, uteområder

Naturområdene hvor boligene blir regulert, benyttes i liten grad til nærrekreasjon som turgåing i dag. Mens områdene i sør som reguleres til friområde, benyttes i dag som gangatkomst til Repstadvannet.

5.8 Landbruk og kulturlandskap

Det er steingjerder i sørøstlige del av planområdet, men ellers er det ingen registrerte kulturlandskapselementer i planområdet.

5.9 Trafikkforhold

- Vegsystem

For å komme til området, kjører man av fra E39 i Lundekrysset, og følger fv. 204 og fv. 114 vestover til kryss fv. 302. Deretter følges fv. 302 nordover til kryss kommunal veg Vedderheia som følges videre inn til feltet. Bredden på kommunal atkomstvegen fram til planområdet varierer, men er ca. 5,5 meter. Det siste vegstykket før nytt kryss til Felt B22 ble etablert for noen få år siden da boligområdet Vedderheia Nord ble etablert.

Figur 12, ny atkomstveg, mot vest fra hovedvegen.

- Trafikkmengde og skiltet hastighet

Skiltet hastighet i Vedderheia er 30 km/t.

- Ulykkessituasjon

Det er ingen registrerte trafikkulykker på kommunal veg i Vedderheia.

- Trafikksikkerhet for myke trafikanter

Det er atskilt gang- og sykkelveg langs kommunal veg i Vedderheia helt frem til avkjørsel til felt B22. Videre er det atskilt gang- og sykkelveg langs fv. 302 til Tinntjønn skole og videre til Lunde.

- Kollektivtilbud

I dag går det bussrute til Vedderheia nord. Ruta har endepunkt like nord for planområde «Felt B22».

5.10 Barns interesser

Barns interesser er i stor grad knyttet til friluftsinteressene og bruk som rekreasjonsområde. Det er etablert en atkomststi i søndre del av planområdet som går ned til Repstadvannet og en som går til et stort lekeområde på østsiden av hovedvegen i Vedderheia.

5.11 Sosial infrastruktur

- Skolekapasitet

I år 2009 ble det utarbeidet en skolebruksplan for Søgne kommune. Prognosene er utarbeidet i samarbeid med rådmannens stab i Kristiansand kommune.
Lunde skole bygges ut nå, og forventes å stå ferdig ved årsskiftet 2016/2017. Kapasiteten på Lunde skole er bra.
Ungdomsskolen Tinntjønn har også god kapasitet. I tillegg pågår det nå planlegging av nytt skolesenter på Tangvall. Dette vil gi god kapasitet for ungdomsskolen i nærmeste fremtid.

- Barnehagedekning

Innenfor planområdet er det ingen barnehager. Men i Vedderheia er det 2 barnehager.
Espira Vedderheia barnehage består av 3 avdelinger og ligger i Skytterveien ca. 700 meter fra planområdet. Det pågår planlegging om utvidelse med flere nye avdelinger for barnehagen. Dette vil gi god kapasitet.
Lisebo familiebarnehage har 10 plasser og ligger i Vedderheia 20 ca. 1100 meter fra planområdet.

5.12 Universell tilgjengelighet

Området er ikke opparbeidet i dag og således ikke tilrettelagt med universell utforming.

5.13 Teknisk infrastruktur

- Vann og avløp

I planområdet er det ingen vann eller spillvannsledninger. Det går en vannledning (VL160) gjennom boligfeltet «B17». Spillvann fra boligfelt «B17» m.fl. går i pumpeledning fra kommunal pumpestasjon ved vendehammer, og ut til hovedvegen i Vedderheia Nord.

- Overvann

Det er ingen overvannsledninger i planområdet, men det er overvannsutløp til terreng ved snuhammer i «B17». Planområdet skråner mot vest og sør, med tilsvarende eksisterende avrenning.

- Trafo

Innenfor planområdet er det ingen trafo, men Agder Energi nett AS (AEN) har en nettstasjon (23004-Vedderheia Nord) øst for planområdet. Denne er forsynt med 22 kV jordkabel, og videre som jordkabel i tilstøtende boligfelt «B17» med lavspent 400V. Kapasiteten på eksisterende anlegg er begrenset og må sannsynligvis forsterkes.

- Energiforsyning og alternativ energi, fjernvarme m.m

Vest for planområdet langs Repstadveien har AEN en 22 kV linje som luftspenn.
Det eksisterer ikke alternativ energikilde i planområdet.

5.14 Grunnforhold

- Stabilitetsforhold

Planområdet i vest består av tynt humus-/torvdekke, og søndre del består av bart fjell med stedvis tynt dekke (NGU).

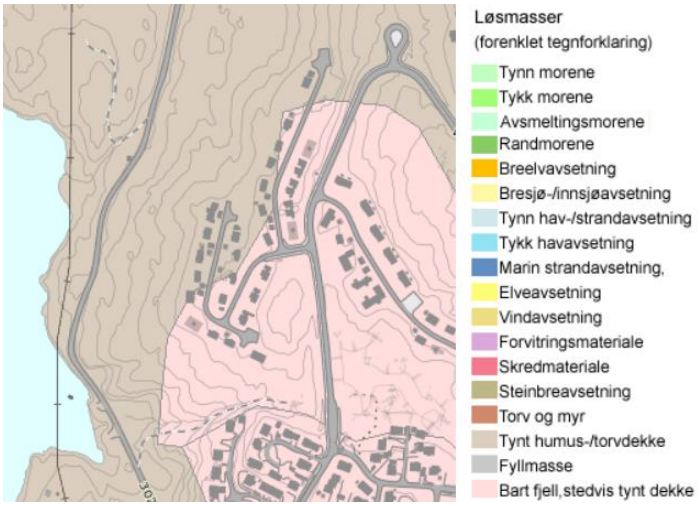

Figur 14, Løsmassekart fra NGU.

5.15 Støyforhold

Det er liten trafikkmengde på de kommunale veger inn til planområdet, og det vil ikke være målbare verdier for støy på disse vegene.
Det er gjennomført støyvurderinger i forbindelse med reguleringsplan/byggeplan Vedderheia Nord som viser at planområdet ikke er berørt.

Kommunedelplan for E39 Volleberg-Døle bru er vedtatt. Det pågår nå utarbeidelse av reguleringsplan for denne parsellen med tilhørende støysoneutredning. Foreløpig utredning viser at planområdet Felt B22 vil ligge utenfor støysonen fra ny E39-trase.

Statens vegvesen har utarbeidet støysonekart for fv. 302. Støy fra fylkesvegen vil ikke få innvirkning på planområdet.

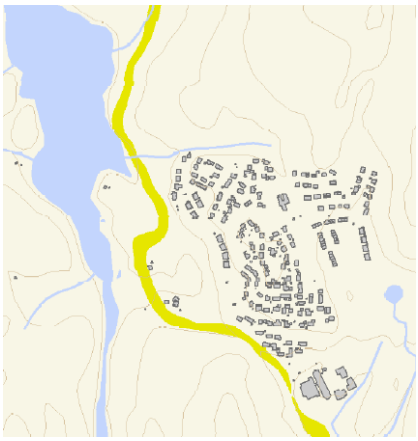
Figur 15, støysonekart fra Statens vegvesen.

5.16 Risiko- og sårbarhet (eksisterende situasjon)

Det er ikke avdekket spesielle forhold innenfor risiko- og sårbarhets analysen i planområdet.

6 Beskrivelse av planforslaget

6.1 Planlagt arealbruk

Planområdet har 3 hovedformål; bebyggelse, samferdsel og grønnstruktur. Dette er i samsvar med reguleringsplan Vedderheia Nord.

Hovedatkomsten til feltet blir fra eksisterende veg Vedderheia. Dette er i samsvar med overordnet reguleringsplan.

Sørøst i planområdet ligger et stort offentlig friområde, med lett atkomst fra nord, vest og sør. Den ene delen ligger i tilknytning til eksisterende friområde i mot nord, og andre ligger i tilknytning til en stor grønn korridor fra boligfeltet og videre mot vest og ned til Repstadvannet.

Det er i tillegg 3 mindre friområder som er fordelt i planområdet. Ny sandlekeplass er plassert i nordre del som også gir kort avstand til tilstøtende boligfelt i øst. For å lette atkomsten til tilstøtende friluftsområder i vest, er det midt i planområdet regulert en kombinert grønnstruktur overvann/grønnstruktur som kan benyttes til snarveg/gangtråkk.

6.2 Gjennomgang av aktuelle reguleringsformål

- Boligbebyggelse

Det er i planen regulert for 22 boenheter, og mulighet for inntil 10 sekundærleiligheter. Alle boligene har nærhet til rekreasjonsområder. Lys og sol er viktige elementer i forhold til områdenes beliggenhet.
Det åpnes for en maksimal utnyttelsesgrad på BYA = 40 % BYA.

- Øvrige kommunaltekniske anlegg

Området er offentlig og skal benyttes til pumpestasjon for spillvann og til trafo.

- Lekeplass

Det etableres en sandlekeplass som legges i tilknytning til friområde. Lekeplassen får en sentral beliggenhet mellom planforslaget og tilstøtende boligfelt (B17).

- Veg

Veg «o_SV1» er kommunal veg og går gjennom planområdet og forbinder eksisterende hovedveg i Vedderheia Nord og Felt B17. Vegen ligger sentralt i planområdet og godt i terrenget uten stor eksponering.
Veg «f_SV1» er felles privat veg og er atkomst til de 3 nordligste boligtomtene i «BFS1». Det er regulert snø opplag i enden av vegen.

- Gang-/sykkelveg

I forbindelse med nytt kryss fra hovedveg gjennom Vedderheia Nord, må fortauet legges om. Pga få boliger er det ikke regulert fortau langs atkomstvegen inn til selve boligtomtene.

- Annet veggrunn – teknisk anlegg

Arealene omfatter nødvendig sideareal til vegene slik som rekkverksrom, grøft, skråning/skjæring mm. Inne i selve boligfeltet er det avsatt 1,5 meter på hver side av kjørevegen.

- Parkering

I planområdet er det sentralt i søndre del av planområdet regulert offentlig gjesteparkering «o_SPP1». Til sammen 6 parkeringsplasser, hvorav 1 er HC-parkering.

- Friområde

Områdene «o_GF1 - o_GF5» er regulert til grøntområde og det åpnes for tilrettelegging med stier og rekreasjon i områdene.

- Angitt grønnstruktur kombinert med andre angitte hovedformål (overvann/grønnstruktur)

Område «o_GAA1» er regulert til kombinert overvann/flomveg. Det tillates gangtråkk til tilstøtende friluftsområde i området.

6.3 Bebyggelsens plassering og utforming

Boligfeltet ligger vest for eksisterende boligfelt i et skrånende terreng.
Boligstrukturene følger etter samme prinsipp som tilgrensende boligfelt med boligene orientert rundt lett tilgjengelig vegsystem. Adgang til boligfeltet skjer i nytt kryss fra sør. Man kan også komme til feltet via det allerede etablerte boligområdet i øst, B17.

Alle boligene, både øst og vest for adkomstvegen har inngangssone med garasje fra vegen. De fleste boligene ligger slik at de tar opp terreng. Boligene vest for vegen har en underetasje. Mens boligene øst for vegen har en andre etasje.

Bebyggelsen er tenkt plassert slik på tomtene at det dannes hage /oppholdssoner mot sør og vest. Tomtene vest for vegen blir liggende på fylling. Det etableres en natursteinmur i fyllingsfoten med synlig høyde 2 meter. Fyllingsskåningen har helning 1:1,5 som angitt i illustrasjonsplanen.

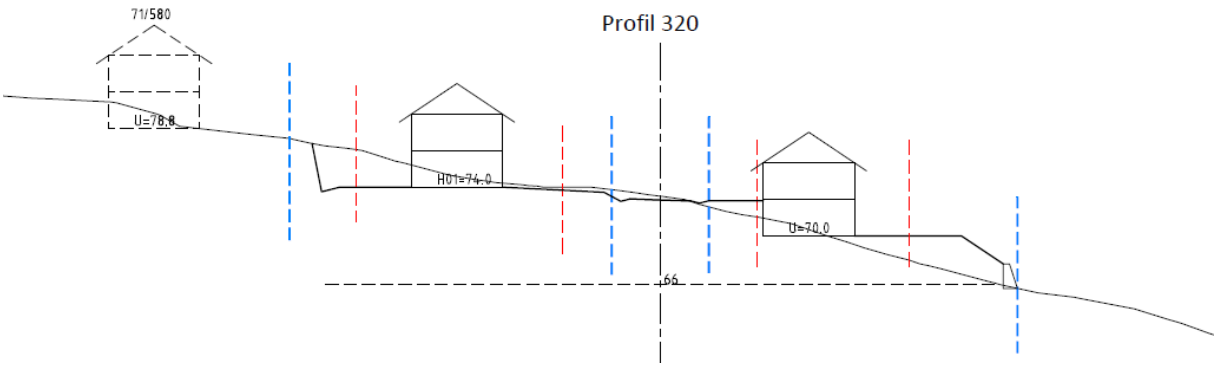

Figur 16, Snitt av tomter og veg.

Bestemmelsene sikrer en enhetlig utforming av bebyggelsen med hensyn til fasader, takform, farger og materialbruk innenfor planområdet. Bebyggelsen skal ha matte, ikke reflekterende tak. BYA er 40% pr regulert tomt.

Reguleringsplanen legger opp til 22 boligtomter. I felt BFS1 er det tillatt med en sekundærleilighet pr tomt. Boligene må plasseres innenfor byggegrense. Det tillates etablert terrasser, murer, garasje, gjerder og boder utenfor byggegrense.
Reguleringsplanen oppgir høyde laveste gulv «TLG» og høyeste tillatte mønehøyde «M».

Murer på boligtomter skal utformes i naturstein og ikke være høyere enn 2 meter.

6.4 Boligmiljø/ bokvalitet

Boligene er plassert slik at det skapes et felles gateløp som alle boligene henvender seg til. Samtidig har alle tomtene muligheten for å opparbeide en solrik uteplass som vil være relativt usjenert og ha god utsikt. Dette er med på å øke bokvaliteten i området.

Boligfeltet har direkte kontakt med skogområder med stier som gir videre koblinger til større friområder, lekeplasser og interne gangveier. Det er også kort avstand ned til Repstadvannet som er godt egnet som badevann.

Innenfor planområdet er det lagt opp til ny sandlekeplass. Det etableres gangveier mot sør som er en videreføring av eksisterende løsninger i boligområdene mot øst. Disse binder skogområdene og eksisterende boligfelt sammen med det nye boligområdet

6.5 Folkehelseloven

Det er gode rekreasjonsområder tilknyttet planområdet. Lekeplassen (o_BLK1) ligger i nordre del av planområdet og i tilknytning til friområde (o_GF2), og er samtidig nær opp til tilstøtende boligfelt. Lekeplassen er et godt treffsted for barnefamilier. Den ligger lyst og solrikt til, med utsikt utover vannet.

Det er regulert 2 store friområde i sørøst (o_GF4 og o_GF5) med gode rekreasjonsmuligheter sommer og vinter. Denne er i direkte tilknytning til et stort friområde mot nord, og en forlengelse av tilstøtende friluftsområde mot vest og ned til Repstadvannet. Det er etablert turdrag vestover. Vannet egner seg som rekreasjonsområde for bading, padling, fisking og spaserturer langs vannkanten.

Øst for planområdet er det etablert en større kvartalslekeplass med bl. skatebane, stier for terrengsykling mm.

Det er svært gode turmuligheter i nærområdet. Tinntjønnløypa (4km lang) og merkede turstier og turveger til Repstad, Lindåsen og Tangvall.

Figur 17, rekreasjon ved Repstadvannet.

Figur 18, eksisterende sti fra boligområdet og ned til Repstadvannet.
Figur 19, eksisterende rekreasjonsområde mellom boligområdet og vannet.

Nærmeste matbutikk er ved området Lunde. Litt øst for Lunde sentrum ligger Søgne kirke, Heimklang og andre forsamlingshus.

Planområdet er tilrettelagt for gående og syklende til og fra skolene og barnehage. Myke trafikanter har trygg ferdsel i sitt nærområde med godt utbygd gang-/sykkelnett.

Det er meget kort avstand til kollektivtrafikk. Buss kjører på hovedveien i Vedderheia Nord og det er bussholdeplasser på begge sider av veien rett øst for planområdet ved nytt kryss til området.

Planområdet ligger vestvendt i god avstand til havet. Åsryggene mot vest og øst er høyere enn boligområdet, og blir dermed noe skjermet for vær og vind. Nærmeste registreringer for klimastatistikk er Oksøy fyr. Vindrosen nedenfor viser fordeling av vind gjennom en periode på 30 år.

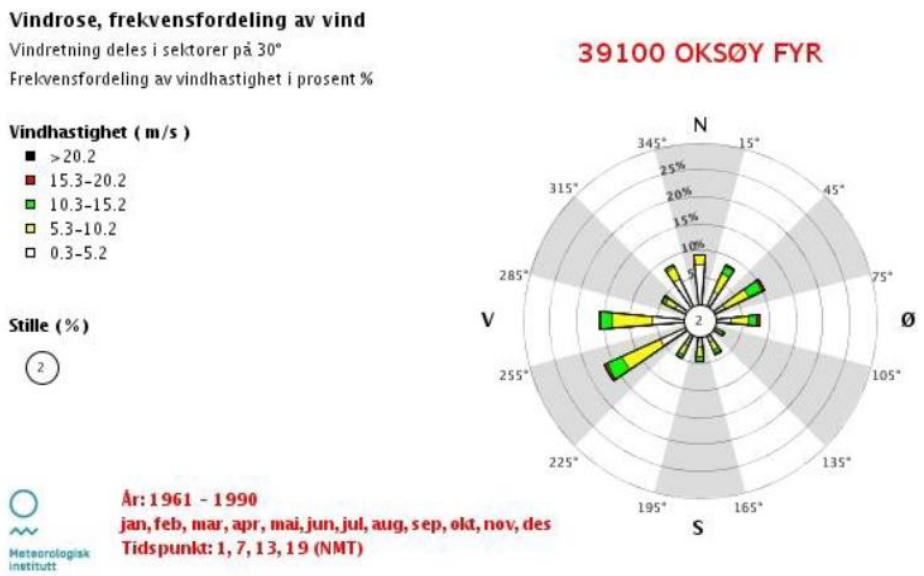

Figur 20, vindrose for Oksøy fyr.

I h.h.t. databasen miljøstatus, er grunnen ikke forurenset.
De viktigste kildene til lokal luftforurensning er veitrafikk, vedfyring, industri og bygg- og anleggsarbeid, med veitrafikk som den største årsaken til lokal forurensning. Det er særlig svevestøv (PM10 og PM2,5) og nitrogenoksider (NO2 og NO) som bidrar til lokal luft-forurensning og som er de største helsetruslene.

Det er ikke industri med forurensning til luft i nærområdet. Avstand til næringsområdet på Lohnelier er ca. 2 km. Hele nærområdet er i hovedsak boligområder med kort avstand til skogsområder og nærhet til vann som rekreasjonsområder. Vedderheia, Repstadveien, Lundeveien og Leireveien er hovedatkomstvegen ut til E39. Det en avstand på ca. 3 km. Planområdet er ikke støyutsatt.

Det er ingen serveringsvirksomheter innenfor eller i nærheten av planområdet som kan medføre lukt eller støy. Det er heller ikke større arrangementsarenaer, foruten Tinntjønn ungdomsskole skole med tilhørende fotballbane. Skolen ligger bak en åsrygg sørøst for planområdet med en luftlinje på 800 meter. Eventuell støy vil ikke påvirke planområdet. Ved skolen ligger Tinntjønnhallen, som brukes til forskjellige ballaktiviteter gjennom hele året.

Planforslaget forholder seg til overordnet plan, og tilstøtende rekreasjonsområder blir ikke negativt påvirket.

6.6 Parkering

Det skal avsettes 2 parkeringsplass pr. boenhet med mulighet for minst en garasjeplass pr. boenhet på egen tomt. Der hvor det er sekundærleilighet skal det i tillegg avsettes 1 parkeringsplass på boligtomta.
Sentralt i feltet er det regulert 6 gjesteparkeringsplass hvorav 1 er HC-plass.

6.7 Tilknytning til infrastruktur

Det skal utarbeides teknisk plan for alle arealer regulert til samferdselsanlegg og teknisk infrastruktur. Tekniske planer for vann og avløp skal omfatte hele planområdet med nødvendige tilknytninger til eksisterende nett. Samferdselsanlegg og teknisk infrastruktur skal anlegges som vist på plan og i samsvar med gjeldende kommunale retningslinjer.

I planområdet reguleres en ny kommunal veg med nytt kryss til vegen i Vedderheia Nord. Den nye vegen tilkobles også eksisterende boligfelt B17 slik at det blir mulig å komme til feltet via B17.

6.8 Trafikkløsning

- **Kjøreatkomst**

Boligområdene «BFS1-4» tilknyttes regulert kommunal veg vedderheia i fra sør/øst.
De 3 nordligste boligtomtene i «BFS1» tilknyttes kommunal veg med felles privat veg.

- **Utforming av veger**

Vegene er dimensjonert etter vegnormal for Søgne kommune.
Kommunal veg «o_SV1» er regulert som atkomstveg med vegbredde 5,0 meter. Inne i boligområdet er maksimal stigning på vegen 5%, minste vertikalkurvatur 700 meter og minste horisontalkurvatur er 20 meter. Fra eksisterende kjøreveg og til boligene har vegen maksimalt 8 % fall dersom det nye krysset benyttes. Dersom krysset til eksisterende Felt B17 benyttes, har vegen maksimalt 5 % fall.

Felles privat veg «f_SV1» er regulert som med vegbredde 3,5 meter. Maksimal stigning på vegen i området er 5%.

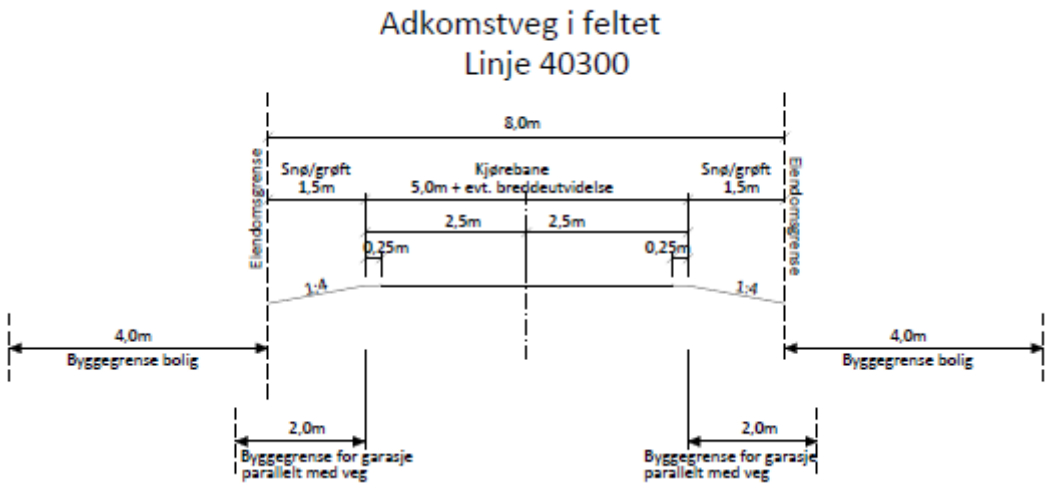

Figur 21, typisk normalprofil av ny kommunal veg (o_SV1).

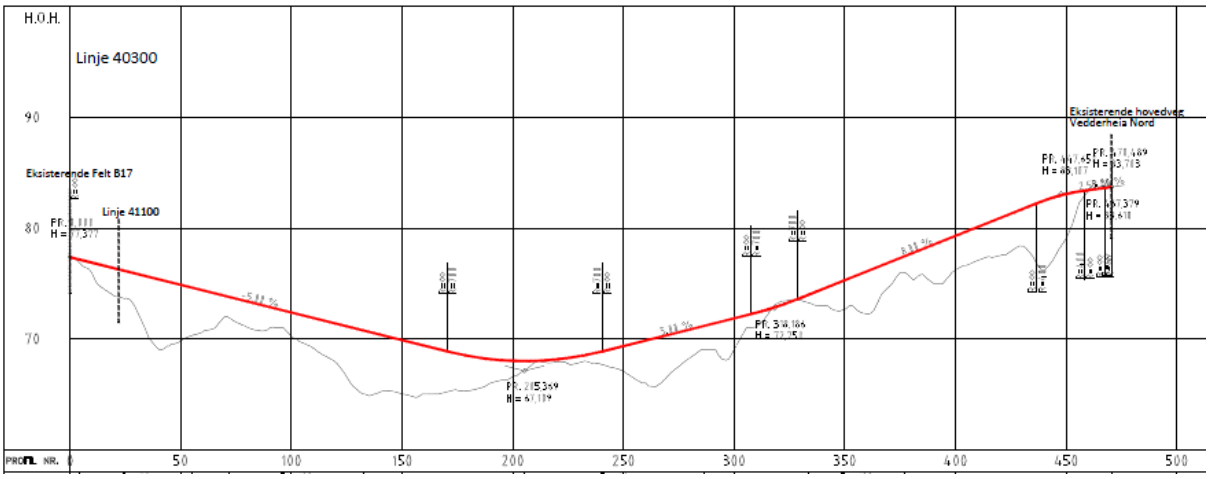

Figur 22, lengdeprofil ny kommunal veg (o_SV1).

- **Tilgjengelighet for gående og syklende**

Øst for planområdet langs hovedatkomstvegen «Vedderheia» er det etablert fortau. Inn ii planområdet er det ikke regulert fortau da det er få boliger og trafikkmengden er liten.
I tillegg er det lagt opp til turstier i friluftsområdet som kan benyttes som snarveier i området.

- **Felles atkomstveger, eiendomsforhold**

Veg «f_SV1» privat felles atkomstvei til 3 boliger er felleseie.

6.9 Planlagte offentlige anlegg

Foruten ny kommunal veg, parkeringsplasser, lekeplasser, friområde og trafo/pumpestasjon, er det ikke planlagt andre offentlige anlegg i planområdet.

6.10 Miljøoppfølging

Den enkelte boligtomt holder renovasjonsdunker, som settes ut mot veg på tømmedag. Sortering av avfall som plast, metall og klær leveres ved etablerte returpunkt i kommunen. Plan for avfallshåndtering i Søgne kommune skal følges.

6.11 Universell utforming

Veien er universell utformet og minimum 50 % av boligene blir utformet med universell atkomst til bolig og med hovedfunksjonene på inngangsplan. Dette er sikret gjennom bestemmelsene og gjelder felt BFS1.

6.12 Uteoppholdsareal

Innenfor planområdet er det regulert et fellesareal o_BLK1 som er en sandlekeplass. Sandlekeplass er plassert på en lett tilgjengelig flate med innkjøring i nord og er

dimensjonert slik at den kan inneholde huske, sandbasseng, sklie og oppholdssone med benk.

Alle tomtene har mulighet for å opparbeide en solrik uteplass som vil være relativt usjenert og ha utsikt.

6.13 Landbruksfaglige vurderinger

Det er ingen landbruksarealer innenfor planområdet.

6.14 Kollektivtilbud

I detaljreguleringsplanen er det ikke tilrettelagt for kollektiv. I overordnet reguleringsplan Vedderheia Nord er det tilrettelagt satsing på kollektivtilbudet. Nærmeste bussholdeplass ligger i tilknytning til hovedvegen ved nytt kryss til Felt B22. Her er det bussholdeplass på begge sider av vegen. Avstand fra nærmeste nye boligtomt er ca. 100 meter. Tilrettelegging for bruk av buss fremmer miljøet.

6.15 Kulturminner

Vest-Agder Fylkeskommune v/ fylkeskonservator har gjennomført befaring i forbindelse med reguleringsplan Vedderheia Nord og avklart dette planområdet. Det er ikke registrert automatiske fredete kulturminner innenfor planområdet, og fylkeskonservator har ingen andre merknader.
Detaljplanen er dermed ikke i konflikt i forhold til kulturminner.

6.16 Plan for vann- og avløp samt tilknytning til offentlig nett

- **Vann**

Hovedvannledningene i området skal dimensjoneres for å kunne tilfredsstille krav til brannvann på 20 l/s (småhusbebyggelse). I tillegg foreslås å etablere ringledning gjennom området for å gi en ytterligere sikring av både drikkevann og brannvannforsyning.

- **Avløp**

Spillvann (avløpet) føres til pumpestasjon via selvfallsledninger. Det foreslås å flytte eksisterende spillvannpumpestasjon i vendhammer i «B17» til ny plass i «B22». Dette betyr at det legges ny pumpeledning i veg ut til hovedveg.

- **Overvann**

Overvann vil bli ført via ledninger til terreng. Tomter på innsiden av ny veg tillates å føre overvann via kommunalt ledningsnett til terreng (o_GAA1), øvrige tomter skal fordrøye lokalt/infiltrasjon.
Det er regulert inn eget flomløp (o_GAA1) som skal sikre at tomter/bygninger ikke blir vesentlig berørt dersom øvrig overvannsnett blir tett/overbelastet.

Eksisterende overvannsledning (OV600) som kommer ut i terreng rett ved ny avkjørsel i øst, forlenges.

6.17 Avbøtende tiltak/ løsninger ROS

Det er utarbeidet en ROS-analyse av planområdet. Det er ikke avdekket spesielle emner som krever avbøtende tiltak/løsninger innenfor planområdet, foruten aktsomhet for radon. I byggeperioden bør det etableres radonsperre for hver bolig.

6.18 Rekkefølgebestemmelser

Det stilles krav om opparbeidelse av lekeplass og atkomstveg, samt nytt kryss på eksisterende E39. Det vises for øvrig til reguleringsbestemmelsene.

7 Virkninger/konsekvenser av planforslaget

7.1 Overordnede planer

Forslaget til detaljregulering følger reguleringsplan for Vedderheia Nord.

7.2 Landskap/bebyggelse

For å kunne opparbeide et tilfredsstillende uteareal på tomtene og et helhetlig boligområde, foreslås det å etablere en sammenhengende natursteinmur mot eksisterende terreng i vest. Utformingen av muren er avgjørende for hvordan det nye landskapet vil framstå for omgivelsene.
Vegforbindelsen i sør vil reduserer kontakten mellom eksisterende grøntdrag og lekeplass til stisystem og grøntdrag i sydøst. Det er viktig at stisystem beholdes.

7.3 Stedets karakter

Skogsterrenget transformeres til et rent boligområde med eneboligfelt, jf overordnet paln.

7.4 Estetikk

Det er tatt hensyn til den tilgrensende bebyggelsen i utforming av planen.

Bestemmelsene sikrer at utformingen skal gi en visuell helhet for hver av de nye feltene gjennom bevisst materialbruk, fargebruk og takform.

Det planlagte inngrepet medfører forandring i skråningen mot vest. Det vil være avgjørende for boligområdets uttrykk at man får til en sammenhengende og helhetlig terrengbehandling av skråningene – særlig mot vest, og sammenhengende grønne drag med stedlige masser og vegetasjon.

Boligområdets utforming der boligene plasseres inn i terrenget og tar opp en etasjehøyde er godt tilpasset det eksisterende landskapet.

7.5 Kulturminner og kulturmiljø, evt. verneverdier

Det er ikke registrert kulturminner eller kulturmiljø, og planforslaget gir dermed heller ingen påvirkning/konsekvens.

7.6 Forholdet til kravene i kap II i Naturmangfoldloven

Planområdet er vurdert i forhold til naturmangfoldloven, og det er ikke registrert forhold som vesentlig kan skade naturmangfoldet.

- Naturverdier

Det er ingen registrerte naturverdier innenfor planområdet.

- Biologisk mangfold

Det er ikke registrert spesiell verdifull naturverdi, fugler eller planter i artsdatabanken.

- Verdifull vegetasjon

Det er ikke registrert spesiell verdifull vegetasjon i artsdatabanken.

- Viltinteresser

Det er ikke registrert spesielle viltinteresser, og planforslaget medfører ikke konsekvenser for natur og miljø.

- Økologiske funksjoner osv

Det er ikke registrert noen spesielle økologiske funksjoner i planområdet.

7.7 Rekreasjonsinteresser/ rekreasjonsbruk

Boligfeltet har gode rekreasjonsmuligheter. Det er direkte kontakt med skogområder med stier som gir videre koblinger til større friområder, lekeplasser og interne gangveier. Innenfor planområdet er det lagt opp til ny sandlekeplass. Det etableres gangveier mot sør som er en videreføring av eksisterende løsninger i boligområdene mot øst. Disse binder skogområdene og eksisterende boligfelt sammen med det nye boligområdet.

7.8 Uteområder

Da bebyggelsen henvender seg mot felles gateløp og nabofelt, gir det grobunn for et godt bomiljø.

Boligområdet har gode uteområder både på hver enkelt tomt og fellesareal.
Sandlekeplass er plassert sentralt på en lett tilgjengelig flate.
Alle tomtene har muligheten for å opparbeide en solrik uteplass som vil være relativt usjenert og ha utsikt. Garasjene er plassert slik at de er med på å skape naturlige avgrensninger mot nabotomtene.

Boligområdet ligger godt med tanke på tilgang til omkringliggende skog/grøntdrag og omkringliggende opparbeidede soner med lek og gangveier.

7.9 Trafikkforhold

- Vegforhold

Infrastrukturen gir sikre og gode forhold for både kjørende og gående i området.

- Trafikkøkning/reduksjon

Det er planlagt 22 nye boliger som påkobles eksisterende kommunal veg Vedderheia. Dette er i tråd med overordnet reguleringsplanen.
Nytt kryss i sør medfører at eksisterende boligfelt B17 vil få liten endring av trafikk i feltet.

- Kollektivtilbud

Ingen endring av eksisterende løsning for kollektivtrafikken i området.

7.10 Barns interesser

Barns interesser er ivaretatt i planen gjennom å tilrettelegge for trygg skoleveg, lekeplass, og gangveier med kopling til eksisterende boligområder. I tillegg er området knyttet sammen med flere andre etablerte boligfelt. Dette er positivt med tanke på at det vil være mange barn i nærområdet.

7.11 Sosial infrastruktur

- Skolekapasitet

Søgne kommune har gjennomført en utredning i forhold til kapasitet og behov for utvidelse av eksisterende skoler / etablering av ny skole.
Forslag til detaljregulering er en del av Vedderheia Nord utbyggingen og utgjør en del av det totale boligbyggeprogrammet. Kapasitet for skolene Lunde og Tinntjønn tar høyde for hele Vedderheia Nord. Størrelse og tidspunkt for en eventuell utbygging/ombygging av skolene må vedtas av Søgne kommune.

- Barnehagekapasitet

Da eksisterende barnehage Espira skal bygges ut, vil barnehagekapasiteten være god i området.

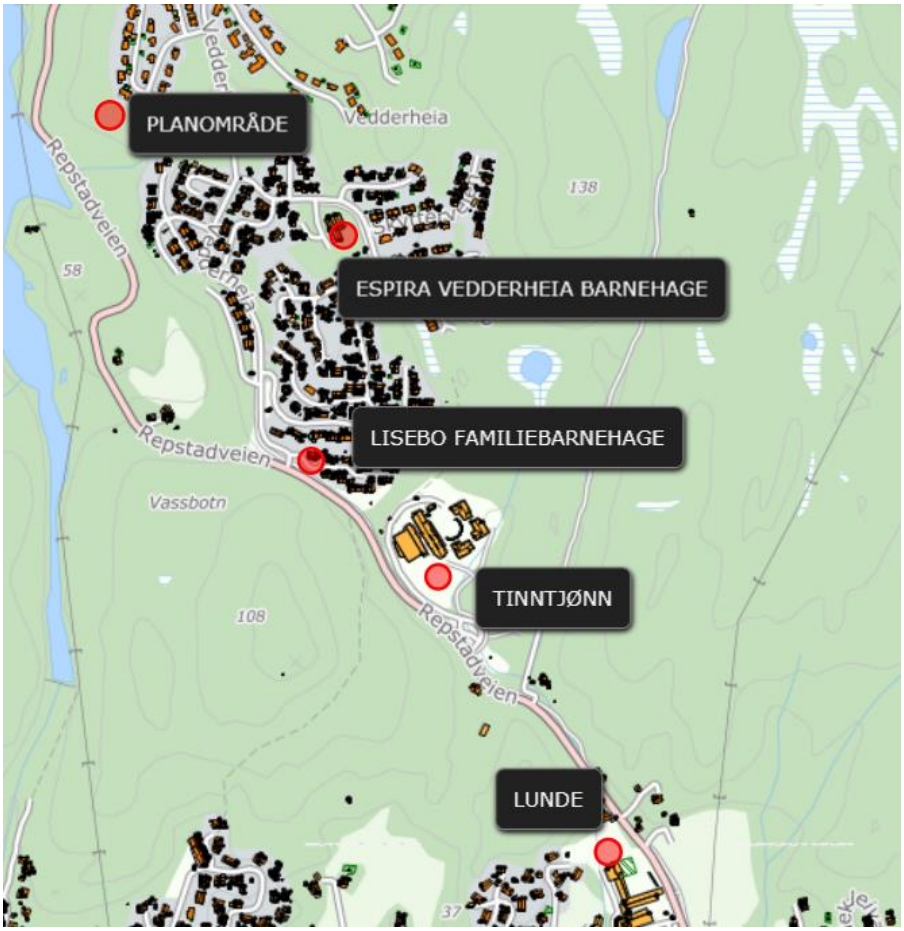

Figur 23, oversikt barnehager og skoler ved planområdet.

7.12 Universell tilgjengelighet

Universell tilgjengelighet er sikret gjennom bestemmelsene ved at FELT BFS1 har alle hovedfunksjoner på inngangsplan. Lekeplassen er lokalisert på et flatt område slik at den kan utformes etter kravene for universell utforming.

7.13 Energibehov - energiforbruk

Energibehov for boligområdene er i hovedsak strøm og vedfyring. Nye boliger skal kunne klare seg med mindre energibruk, og nye boliger skal kunne bruke fornybar energi til oppvarming. Transport for lengre avstander foregår med bil og buss. Transport for kortere avstander er med sykkel.

7.14 ROS

Det er utarbeidet ROS-analyse som vedlegg til planbeskrivelsen. Det er ikke avdekket spesielle virkninger/konsekvenser i forbindelse med planforslaget. Det vises til analysen som vedlegg til plan.

7.15 Teknisk infrastruktur

- **Vann og avløp**

Etablering av ringledning på vann vil forbedre sikkerheten ved eventuell brann.

Planforslaget omfatter flytting av eksisterende spillvannpumpestasjon. Det må etableres større nødoverløpstank da det nå blir ca. 20 ekstra boliger tilknyttet anlegget.

- **Overvann**

Overvann i utbyggingsområdet føres til terreng.

7.16 Drift og vedlikehold

Vegen gjennom området er en gjennomkjørbar og vil således være lett å brøyte. Det er regulert 1,5m annet vegareal på begge sider av vegen gjennom feltet som kan benyttes til snø opplag. I nord er det er regulert en felles veg med snø opplag i enden av vegen.
I forbindelse med kryss og parkeringsplass er det arealer som kan benyttes til snø opplag.

7.17 Økonomiske konsekvenser for kommunen

Detaljregulering Vedderheia nord felt B22 vil tilføre markedet tomter som vil være attraktive både for personer som bor i Søgne eller som vurderer å flytte til Søgne.
Økonomisk vil nye innbyggere gi kommunen vekst, derav økte skatteinntekter, men også økt tjenestebehov som skole, barnehage osv.
Under utbyggingen vil området gi kommunen inntekter i form av tilkoblingsavgifter og byggesaksgebyrer.

8 Innkomne innspill

Det ble varslet oppstart av detaljreguleringsplan. Nedenfor er det et sammendrag av merknader som berører planområdet.

Merknader fra Fylkesmannen i Aust- og Vest-Agder, v/ miljøvernavdelingen, datert 10.02.2016:

Fylkesmannen kommenterer at virkningene av planen må være beskrevet. Det vises til Naturmangfoldlover § 8 – 12, og det må tas høyde for å begrense risiko for spredning av fremmede arter. Dette må innarbeides i bestemmelsene.
Det vises til FN´s Barnekonvensjonen. Barn og unge skal gis anledning til deltakelse i planprosessen. Planen skal sikre trygge og tilgjengelige arealer for barn i alle aldre. I planen skal det beskrives konsekvenser for barn og unge, samt funksjonshemmede.
Det vises til rundskriv T-2/08 om barn og planlegging, og rundskriv T-5/95B om tilgjengelighet for alle.
Inngrep i grunnen må vurderes i forhold til forurensningsforskriften. Dette må knyttes opp mot massedisponering gjennom planen.
Grenseverdier for støy må overholdes. Det vises til Klima- og miljødepartementets retningslinje T-1442.
Det skal utarbeides en risiko- og sårbarhetsanalyse for planområdet. De arealer det knytter seg fare, risiko eller sårbarhet til i planen, avmerkes som hensynssoner med bestemmelser.

Tiltakshavers kommentar:
Tas til etterretning.

Merknader fra Avfall Sør, datert 11.02.2016:

Avfall Sør anbefaler nedgravd løsning for nye boligområder med mer enn 20 boenheter. Det vises til «Utkast ny Avfallsteknisk norm». Foreløpig er det ingen formelle krav til annet enn dunkrenovasjon.

Tiltakshavers kommentar:
I planforslaget legges det opp til dunkrenovasjon slik som i eksisterende boligfelt.

Merknader fra Agder Energi Nett AS, datert 17.02.2016:

AEN har en nettstasjon i nærheten (23004-Vedderheia nord), forsynt med jordkabel 22kV. Byggegrense til jordkabel er 2 meter fra senterlinje. Atkomst til eksisterende anlegg må opprettholdes.
Kapasitet på eksisterende anlegg er begrenset, forsterkning og eventuelt nybygg av nettanlegg må påregnes. Trase for nettanlegg og areal til nettstasjon må gjøres i samråd med AEN.

Tiltakshavers kommentar:
Det er satt av areal for ny nettstasjon i planområdet.

Merknader fra Statens vegvesen Region sør, datert 22.02.2016:
Statens vegvesen forutsetter at atkomst til området skal være i samsvar med reguleringsplanen for vedderheia nord. Statens vegvesen har ellers ingen merknader i forbindelse med varsel om oppstart av planarbeidet.

Tiltakshavers kommentar:
Atkomst forholder seg til overordnet reguleringsplan.

Merknader fra Vedderheia nord velforening, styret ved Brede Apland, mottatt 02.03.2016:
Beboerne i boligfelt B17 er positiv til utbygging av felt B22.
Det forutsettes at atkomst til feltet blir lagt inn fra busslomma på sletta før innkjøring til felt B17 og B18, og at det skal etableres 20 boenheter.
Repstad Eiendom har uttalt at nye boliger skal ha topp tak lavere enn boligene i felt B17, men at atkomst til felt B22 ikke er bestemt.

Tiltakshavers kommentar:
Atkomst inn til felt B22 reguleres inn fra sør-øst. Det reguleres 22 boenheter.
Det er regulert mønehøyder, se plankart.

Merknader fra ingeniøravdelingen i Søgne kommune, mottatt 08.03.2016:
Det er utarbeidet en ny norm for vann, avløp og overvann som snart er klar for bruk.

Tiltakshavers kommentar:
Tas til etterretning.

Merknader fra Vedderheia velforening, ved leder Asbjørn Sørfonden, mottatt 09.03.2016:
Hovedinnkjøring til det nye feltet bør legges direkte i ny avkjøring fra fv. 302, ca. 1 km vest for krysset inn til vedderheia boligfelt.
Det er i dag mye trafikk i vedderheia boligfelt. Tidligere barnehagetomt er under omregulering til boligformål, som vil øke trafikken i området. Dette gir større trafikk enn hva som lå til grunn i 2010. En ny avkjøring til Vedderheia vil øke trygghet og sikkerhet.

Tiltakshavers kommentar:
Tiltakshaver forholder seg til gjeldende reguleringsplan. Det er ikke åpnet for ny avkjøring fra fv. 302. Atkomst forutsettes gjennom eksisterende vegnett i Vedderheia. Trafikk er vurdert i tidligere planprosess.

Merknader fra Vest-Agder Fylkeskommune, v/ plan- og miljøseksjonen, datert 09.03.2016:
Fylkeskommunen har ingen spesielle merknader til varsel om oppstart av arbeid med ny reguleringsplan, så fremt den er i tråd med overordnet plan.
Det må beskrives hvordan barn og unges interesser blir ivaretatt. Det forutsettes arealmessig tilstrekkelige, attraktive og trygge lekeområder for barn og unge i ulike aldersgrupper. Det bør stilles rekkefølgekrav til opparbeidelse. Snarveger bør opprettholdes.

Fylkeskonservator har foretatt befaring i forbindelse med Vedderheia nord, og avklart hele denne delen. Det er ingen andre merknader.

Tiltakshavers kommentar:
Planforslaget forholder seg til overordnet plan.
Tas til etterretning.

9 Avsluttende kommentar

Føringene gitt i reguleringsplanen Vedderheia Nord er videreført i detaljreguleringen Vedderheia nord felt B22.

I planområdet er det ikke avduket konfliktområder. ROS-analyse er utført. Det anbefales å legge radonsperre for hver bolig. Det er ikke registrert automatiske fredete fornminner i planområdet, og ingen landbruksareal går tapt.

Hovedformålet med detaljreguleringen er tilrettelegging for nye boliger, som vil gi gode oppvekst og bokvaliteter. Området har nærhet til rekreasjonsområder som vann og skogsområder, samt kort avstand til barnehager og skoler. Det er åpnet for snarveger til tilstøtende boligområder og rekreasjonsområder. I tilstøtende planområde mot øst er det tilrettelagt for busskommunikasjon. Universell atkomst er nøkkelord ved prosjektering av nye veger og områder for bebyggelse.

Det er en god balanse mellom boligformål og rekreasjonsområder, samt nødvendig infrastruktur.

Detaljregulering Vedderheia nord felt B22 vil gi Søgne kommune gode, attraktive og kvalitetsrike boligtomter.